CAPÍTULO 18

LA AVENIDA VARGAS Y EL HOSPITAL GENERAL

El Concejo Municipal[1] emite decreto de expropiación (2-2-1952), por causa de utilidad pública, de propiedades situadas en la calle 18 (antigua calle Monagas[2]),

"*... a fin de construir la Avenida José María Vargas, para dar acceso al "Gran Hospital de Barquisimeto" y a las comunidades del lado norte de la Vía Panamericana*[3] ".

De esta forma la historia de la avenida Vargas y del Hospital se unieron entre sí.

[1] El presidente (E) Concejo Municipal es el Dr. Antonio María Pineda Castillo, médico del Hospital "Antonio María Pineda" (el Presidente titular es Ernesto Bensaya Pérez). En junio 1952 el Dr. (Abg.) Esteban Agudo Fréitez asume como nuevo gobernador del Estado Lara y designa al Dr. (Abg.) Juan Antonio Asuaje Alamo como presidente del Concejo Municipal. Las nuevas autoridades continuaron la construcción de la avenida según lo planificado.
Ambos presidentes municipales tienen estrecha relación con el Hospital La Caridad, hoy día Antonio María Pineda. El Dr. Asuaje Alamo es hijo del Dr. Juan Antonio Asuaje Gómez, quien fue médico del Hospital La Caridad y cuya esposa Rosa Amelia Alamo e hija Ana Mercedes Asuaje Alamo fueron miembros de la Sociedad Benefactora del Hospital.

[2] El Plano Regulador de 1946 cambió la nomenclatura de las calles de la ciudad llamándolas calles (de Sur a Norte) y carreras (de Este a Oeste), sustituyendo los nombres propios por números.

[3] El nombre oficial era carretera Panamericana, sección Barquisimeto, pero se le mencionaba en documentos como vía Panamericana y popularmente como "la Panamericana".

Se inician los trabajos (1-9-1952) de construcción de la avenida.

Figura derecha: inicio de las obras de construcción de la avenida José María Vargas (fotografía: prensa local).





Figura izquierda: Calle 18, inicio de movimientos de tierra para construir la avenida Vargas. En el centro, al final de la calle, el edificio del Hospital, ya totalmente levantado. La fotografía aparece en la portada del libro: Arias Bello, Humberto: *Del Hospital de Santiago al Hospital de Pineda.* Edición con motivo de las Jornadas Pineda. Barquisimeto, 1984.

Figura inferior: Reportaje del Diario El Impulso sobre el inicio de la demolición de casas para iniciar la construcción de la avenida José María Vargas.



Figura superior: ampliación de la calle Monagas (Calle 18) para dar inicio a la construcción de la avenida Vargas. Vista desde la Calle del Comercio (Avenida 20) hacia el Hospital General, que se observa en el centro, delante de la silueta del cerro La Ruesga. Fotografía: Prensa local.

La avenida se construye en 2 etapas: desde la carrera 19 hasta el Hospital (inaugurada el 1-6-1954) y desde la carrera 19 hasta la Cuesta Lara (inaugurada el 30-11-1956). Se empezó durante el periodo del gobernador Dr. (Abg.) Carlos Felice Cardót (que pagó las bienhechurías expropiadas),continuó con el Dr. (Abg.) Esteban Agudo Fréitez (inició los trabajos) y se concluyó en el período del TCnel. (Ej) Carlos Morales (la inauguró).

PICTORIAL DE LA CONSTRUCCIÓN DE LA AVENIDA VARGAS
(diferentes fechas y lugares, tomados de reportes de la prensa local)

Figura superior: (1951, fecha imprecisa), movimiento de tierra para la construcción de la avenida Vargas. Hospital al fondo. Camión esparciendo agua (a la izquierda) y tractor movilizando tierra (a la derecha).

Figura inferior: (1951, fecha imprecisa), movimiento de tierra para la construcción de la avenida Vargas. Hospital al fondo. Camión esparciendo agua (a la derecha) y tractor movilizando tierra (a la izquierda).

Figura superior: Movimiento de tierra para construir la Avenida Vargas. Vista desde la redoma hacia el cerro El Manzano (Sur). Fotografía: diario Última Hora, Francisco Villazán y Carrillo, fecha imprecisa.

Figura superior: Vista de la construcción de la avenida Vargas hacia el cerro El Manzano (Sur). La esquina que se observa corresponde a la carrera 19 (fotografía de autor y fecha exacta desconocidos).

Figura Inferior: Movimiento de tierra para construir la redoma (vista Norte-Sur). Fotografía: prensa local, fecha y autor no precisados.



Figura superior: Movimiento de tierra, inicio de la construcción de la avenida Vargas, fecha y autor imprecisos.

Figura inferior: construcción de la avenida Vargas: colocando tuberías y pavimentación en cemento. Hospital General al fondo. Fotografía de Francisco Villazán y Carrillo, diario Última Hora.

Figura inferior: construcción de la avenida Vargas: colocando tuberías y pavimentación en cemento. Vista desde el centro hacia la redoma, fotografía de Francisco Villazán, diario Última Hora.

Figura inferior: 1954, vista al Sur. Reparación de la avenida por hundimiento, ya pavimentada, entre el hospital y la redoma. En el sitio existía una laguna que fue rellenada durante la construcción, pero el terreno quedó flojo y con el paso de los vehículos se hundió.

Figura Superior: redoma en fase final de relleno. Hospital al fondo.

Figura superior: Avenida Vargas en 1954, fase final de la construcción. Vista desde la redoma. Camiones de la época circulando. Aguador regando la isla central. Al fondo el Hospital.

Figura inferior: Vista desde la carrera 26. Brocales de la isla central inconclusos. Palmeras recién sembradas. Al fondo el Hospital General.



Figura inferior: Construcción de la redoma. Vista desde el Hospital hacia el cerro El Manzano (que se observa al fondo). En el extremo superior izquierdo se construirá el edificio de la Unidad Sanitaria. Fotografía: diario El Impulso 1952.

INAUGURACIÓN

La 1ra. etapa (desde la carrera 19 hasta el Hospital) de la avenida José María Vargas fue inaugurada el 1-6-1954 por el Presidente de la República Cnel. Marcos Evangelista Pérez Jiménez.

Así como la construcción del Hospital General originó la creación de la avenida Vargas, puede decirse que recíprocamente, su inauguración originó el inicio de actividades (2da. inauguración) del Hospital. Es la tradición oral, en boca del Dr. Theoscar Sanoja Hernández, a la fecha radiólogo del Hospital "Antonio María Pineda", que el Presidente, al observar que al final de la avenida estaba el edificio del Hospital General, concluido pero aún incompletamente dotado, ordena que se mude el Hospital "Antonio María Pineda" al nuevo edificio, lo cual se termina de materializar con el inicio formal de actividades del nuevo Hospital General de Barquisimeto el 16-11-1954.

Figura inferior: Vista del Hospital General desde La Redoma de la avenida Vargas en 1954. Avenida ya terminada e inaugurada; el Hospital aún no está funcionando.

Figura inferior: la misma toma un año después (1955) con el Hospital funcionando. Véase el tamaño de los arboles en la redoma y los laterales hacia el Hospital.

Figura inferior: Coronación de la Divina Pastora en la redoma de la avenida Vargas (14-1-1956), uno de los tantos eventos que se efectuaron en la avenida en sus 1ros. años. Nótese el Hospital Central de Barquisimeto en el extremo izquierdo de la fotografía (Diario El Impulso).



Figura superior: Redoma de la avenida Vargas ya terminada, fuente en el centro; edificaciones de la feria de Barquisimeto al fondo. Imagen del Hospital General en el extremo izquierdo. Terrenos vacíos donde se construirá el edificio del Colegio de Médicos al centro.

Figura Inferior: Redoma de la avenida Vargas recién inaugurada, esquina NE.

Al inaugurarse (1-6-1954), la Av. Vargas se convirtió rápidamente en el sitio habitual para desfiles y caravanas de la sociedad barquisimetana.

Figura inferior: Desfile de la Sociedad Anticancerosa por la recién inaugurada Av, Vargas en 1954. Vehículos estacionados al comienzo de la avenida, tramo carrera 19 hasta la cuesta del rio (aun no inaugurado), esperando para comenzar el desfile, detrás del moderno carro bomba del también recién inaugurado (8-2-1953) Cuerpo de Bomberos de Barquisimeto. Al fondo la serranía El Manzano.

Tanto la Av. Vargas como el Cuerpo de Bomberos, son iniciativas de médicos del Hospital "Antonio María Pineda": los Drs. Antonio María Pineda Castillo y Ramón Ignacio Méndez Llamozas, respectivamente.

Figura inferior: Redoma de la avenida Vargas, 1954 ya terminada, fuente en el centro; Unidad Sanitaria sin construir. Imagen del Hospital General al fondo.

Figura inferior: La misma imagen anterior un año mas tarde (1955). Es notorio el crecimiento de los arboles alrededor de la redoma. Edificio de la Unidad Sanitaria aún sin construir. Al fondo edificios del Hospital General y de la Escuela de Enfermeras. Mas atrás (en el centro de la foto) el cerro La Ruesga, que por años será un icono en todas las panorámicas que se realizarán al Hospital desde su lado Sur.

Figura inferior: Vista del Hospital General desde la redoma de la avenida Vargas. Destaca el tanque elevado, lado izquierdo de la foto, a la fecha el mas alto de la Ciudad. Fotografía de Mario Navarro*, fechada en 1955. Nótese el crecimiento de los arboles de la avenida en relación a las fotos anteriores.

*** Mario Ramón Navarro González (1912-1988), es un personaje histórico de la ciudad. Se le considera último fotógrafo profesional "placero" de Barquisimeto. Existen numerosas fotografías del Hospital Central de su autoría, así como de otras edificaciones, parques, plazas, calles y avenidas de la ciudad, durante las décadas de 1950 y 1960.**



Figura inferior: Vista de la avenida Vargas, desde la carrera 22, hacia el Norte, en 1956. Al fondo el Hospital Central de Barquisimeto, con el Cerro La Ruesga. La enorme cruz en el centro de la fotografía corresponde a la Farmacia Vargas*, en la carrera 23, esquina NO, convertida en icono de la ciudad, llamada popularmente esquina de la cruz verde. Nótese el tamaño de los arboles en relación a fotografías anteriores (fotografía de autor y fecha exacta desconocidos, rotulada 1956).

*** El regente de la Farmacia Vargas es el Dr. (Far.) Héctor Bosh (ex presidente Asamblea Legislativa del Estado Lara) hasta su fallecimiento cuando es sucedido por la Dra (Far.) Gavidia.**

En la práctica, todas las fotografías de la avenida Vargas en la 2da. mitad de la década de los '50, tenían como referencia el Hospital Central de Barquisimeto y su emblemático cerro posterior. A partir de la década de los '60, se empezará a construir edificios e instalar comercios a ambos lados de la avenida, adquiriendo características propias, y se popularizan fotografías de la misma ya sin la referencia del Hospital.

PICTORIAL DEL FINAL NORTE DE LA AVENIDA VARGAS

Figura inferior: Final Norte de la avenida Vargas (1954), antes de la inauguración del Hospital General.

Figura inferior: Final Norte de la avenida Vargas (1955), nótese la concordancia del estilo de la avenida con la entrada principal del Hospital General, los arboles sembrados a ambos lados y palmeras centrales en crecimiento. También es notorio el movimiento de tierra donde se está ejecutando el Colegio de Médicos (Fotografía: Francisco Villazán y Carrillo, diario Ultima Hora).

Figura inferior: la misma fotografía anterior, tomada en distinto momento, coloreada y comercializada como postal de la época (puede verse en www.todocoleccion.com revisado en 2012).

Nótese en el angulo superior derecho de las fotografías, la edificación "gemela" del Hospital General para la época: el Edificio Nacional (los edificios públicos de mayor volumen y altura de la ciudad). También es notorio el portón derecho cerrado al paso de vehículos, los cuales entraban y salían del Hospital por el mismo portón (Izq), donde había una casilla con vigilante. Como hecho curioso, el portón permanece cerrado los 1ros. 3 años de funcionamiento del Hospital, abriéndose con el cambio de gobierno (y de autoridades del Hospital) en 1958.

Figura inferior: Fotografía fechada 1956 (autor desconocido), tomada desde el Hospital Central, muestra el final Norte de la avenida Vargas).

Figura Inferior. La misma proyección tomada en 1958. Nótese el tamaño de los arboles y las nuevas construcciones a los lados de la avenida, entre ellas el edificio del Colegio de Médicos ya concluido y los 2 portones (entrada y salida) del hospital abiertos.



Este final de la avenida Vargas con el Hospital será modificado (Agosto 1980), cortando el lado Este, en forma diagonal, hasta la calle 17, convirtiendo esta calle a todo lo largo de la cara Este del Hospital, en una vía de 4 canales, llamada prolongación de la avenida Vargas, que conecta con la avenida Libertador (inaugurada en 1973, antes vía Panamericana). En el espacio triangular que quedó (lado superior izquierdo de la fotografía) se construirá una plaza con el nombre de "José María Vargas". La plaza tiene una frondosa mata de caucho en su cara Este, frente al edificio del pedagógico, por lo que será conocida popularmente por los lugareños y estudiantes de la ETI como la «Plaza de la Mata de Caucho», usada frecuentemente por los estudiantes para celebrar sus promociones.

BIBLIOGRAFÍA MENCIONADA EN EL TEXTO:

- Arias Bello, Humberto: *Del Hospital de Santiago al Hospital de Pineda.* Edición con motivo de las Jornadas Pineda. Barquisimeto 1984.

SIGUIENTE:
Capítulo 19. Año 1954. Hospital General de Barquisimeto: Inicio de actividades

ANTERIOR:
Capítulo 17. Hospital General de Barquisimeto Antecedentes – Construcción

COMENTARIOS Y OBSERVACIONES: hcamp-historia@mailfence.com